Manual de Usuario

LIBERTYMAP

Centro de Bachillerato Tecnológico industrial y de servicios 271

Nombre del Proyecto:

LibertyMap

Integrantes:

- **Miguel Alejandro Lerma Rosales**
- **Enrique Gerardo Olazarán Izaguirre**
- **Leonardo López Hinojosa**

6°A

1. ÍNDICE

Contenido

Manual de Usuario 1
1. INDICE 2
2. INTRODUCCION 3
3. OBJETIVO DEL MANUAL 4
4. DESARROLLO 5
4.2.1 Requisitos previos 5
4.2.2 Explicación detallada de cada acción en las Interfaces 10
4.3 Posibles errores y su corrección 20
4.3.1 Errores 20
4.3.2 Corrección 20
4.4 Preguntas Frecuentes 21
5. Datos de contacto 23
6. BIBLIOGRAFIA 24

2. INTRODUCCION

La historia es la lente a través de la cual comprendemos nuestro presente y proyectamos nuestro futuro. Conscientes de la importancia de conocer quiénes fueron los protagonistas y qué hechos marcaron la evolución de nuestros entornos, desarrollamos una aplicación orientada a difundir y contextualizar los sucesos históricos ocurridos en diversas regiones de México.

Esta herramienta surge como respuesta a la dificultad que muchos tienen para acceder a información específica y localizada, pese a la abundancia de recursos disponibles en internet. Aprovechando el desarrollo de páginas web, la robustez de bases de datos y la integración de sistemas de geolocalización, nuestro sistema no solo traza un mapa interactivo con los sitios de relevancia histórica, sino que también ofrece comparaciones entre el entorno actual y el pasado.

El presente manual tiene como fin acompañar al usuario en su recorrido por la aplicación, proporcionando pautas claras para la instalación, el manejo, la corrección de posibles errores y la solución de dudas frecuentes.

3. OBJETIVO DEL MANUAL

El objetivo de este manual es proporcionar una guía completa y accesible para el uso de la aplicación, permitiendo a cualquier usuario, sin importar su nivel técnico, aprovechar todas sus funcionalidades. En particular, este documento busca:

- Explicar de forma detallada el proceso de instalación y puesta en marcha del sistema, asegurando que el entorno (páginas web, servidor y base de datos) se configure correctamente.

- Describir el manejo básico y avanzado de la aplicación, ilustrando cómo navegar por el mapa interactivo, consultar información histórica y utilizar herramientas de búsqueda y filtrado.
- Detallar los posibles errores que pueden surgir durante el uso, ofreciendo soluciones claras y prácticas para corregirlos.

- Responder a las dudas más frecuentes a través de una sección de Preguntas Frecuentes, facilitando así el proceso de resolución de incidencias y ampliando el conocimiento sobre el funcionamiento del sistema.

4. DESARROLLO

4.2.1 Requisitos previos

Requisitos previos

1. Para utilizar correctamente la plataforma LibertyMap, el usuario debe contar con lo siguiente:
2. Dispositivo con acceso a internet, como computadora, laptop, tablet o teléfono inteligente.
3. Conexión a internet estable para cargar el mapa interactivo y el contenido multimedia.
4. Navegador web actualizado, preferentemente:

- Google Chrome
- Mozilla Firefox
- Microsoft Edge
- Safari

5. JavaScript habilitado en el navegador, ya que el mapa interactivo y varias funciones dependen de este.
6. Resolución mínima recomendada: 1280×720 para una visualización óptima del mapa y paneles.

Requisitos Mínimos del Sistema

<u>Hardware:</u>

- **Procesador:** 1.6 GHz o superior
- **Memoria RAM:** 4 GB como mínimo
- **Almacenamiento disponible:** 200 MB libres para caché y archivos temporales del navegador
- **Pantalla:** Resolución mínima de 1024 × 720 px

Requisitos Recomendados del Sistema

Hardware:

- **Procesador:** 2.4 GHz o superior (Intel i5 / Ryzen 3 en adelante)
- **Memoria RAM**: 8 GB
- **Almacenamiento disponible:** 500 MB libres
- **Pantalla:** Resolución Full HD 1920 × 1080 px

Software:

Sistema operativo:

- Windows 10 o 11
- macOS 11 Big Sur o superior
- Android 10 o superior
- iOS 14 o superior
- JavaScript habilitado
- Cookies habilitadas
- Navegadores alternos optimizados: Firefox, Edge, Safari
- ***Navegador recomendado: Google Chrome (versión más reciente)***

Conectividad:

- **Internet recomendado:** 20 Mbps o más, para cargar mapas, filtros y contenido multimedia sin retrasos.

Pasos de Instalación del Navegador Google Chrome:

Puedes usar cualquier navegador web para descargar Google Chrome, en el caso de que no hayas instalado ningún navegador web puedes usar el navegador web instalado previamente en tu sistema operativo como Internet Explorer para Windows y Safari para Mac).

Haz clic en Descargar Chrome, te abrirá la ventana de Condiciones del servicio de Google Chrome.

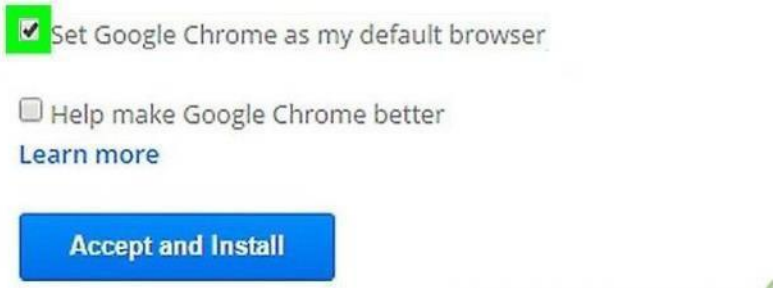

Determina si deseas que Chrome sea tu navegador predeterminado. Si lo configuras como un navegador predeterminado, se abrirá cada vez que hagas clic en el enlace de una página web en otro programa (como en un correo electrónico).

Puedes optar por enviar los datos de uso a Google marcando la casilla etiquetada “Informa tu configuración actual para ayudarnos a mejorar Google Chrome”. Esto enviará los informes de errores, las preferencias y los clics de un botón. No enviará ninguna información personal ni rastreará los sitios web

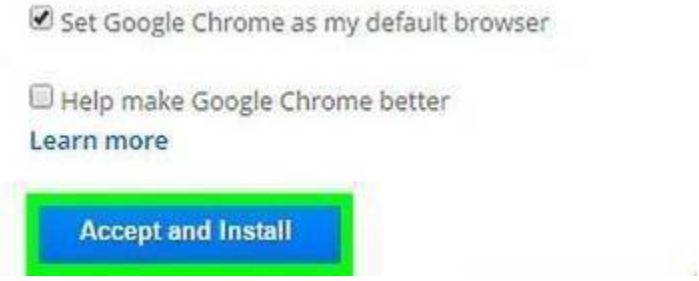

Después de leer las condiciones del servicio, haz clic en “Aceptar e instalar”. Se iniciará el instalador (tendrás instalado Google Chrome cuando termine la operación). Dependiendo de la configuración de tu navegador, tal vez tengas que permitir que el programa se ejecute.

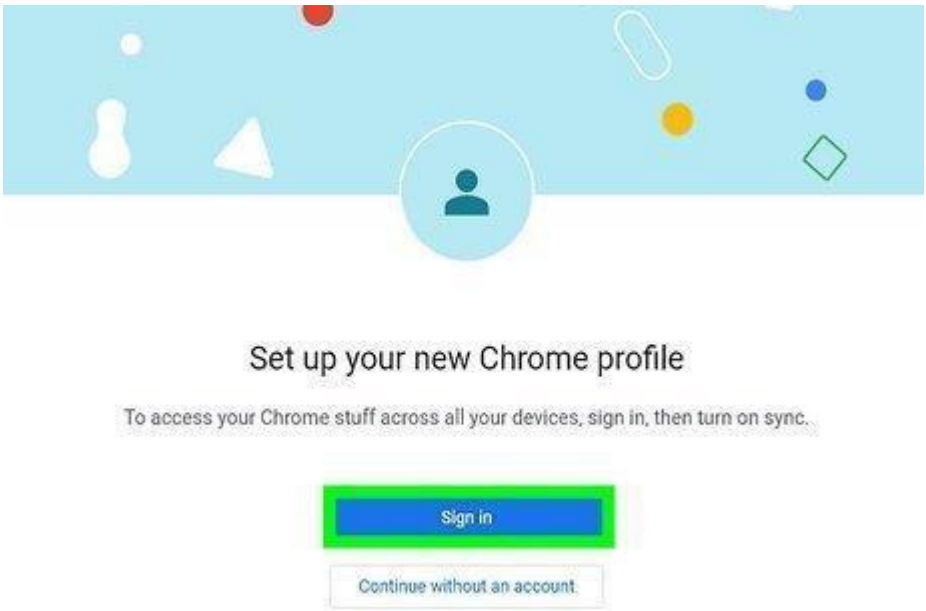

Ingresa a Chrome. Luego de la instalación, una ventana de Chrome se abrirá mostrando la información del uso por primera vez. Puedes ingresar con tu cuenta Google para sincronizar los marcadores, las preferencias y el historial de navegación con cualquier navegador Chrome que uses. Lee el artículo como usar Google Chrome para obtener algunos consejos sobre tu nuevo navegador.

Después de haber hecho cada paso podrás ingresar a Google Chrome y buscar nuestra Pagina Web

4.2.2 Explicación detallada de cada acción en las Interfaces

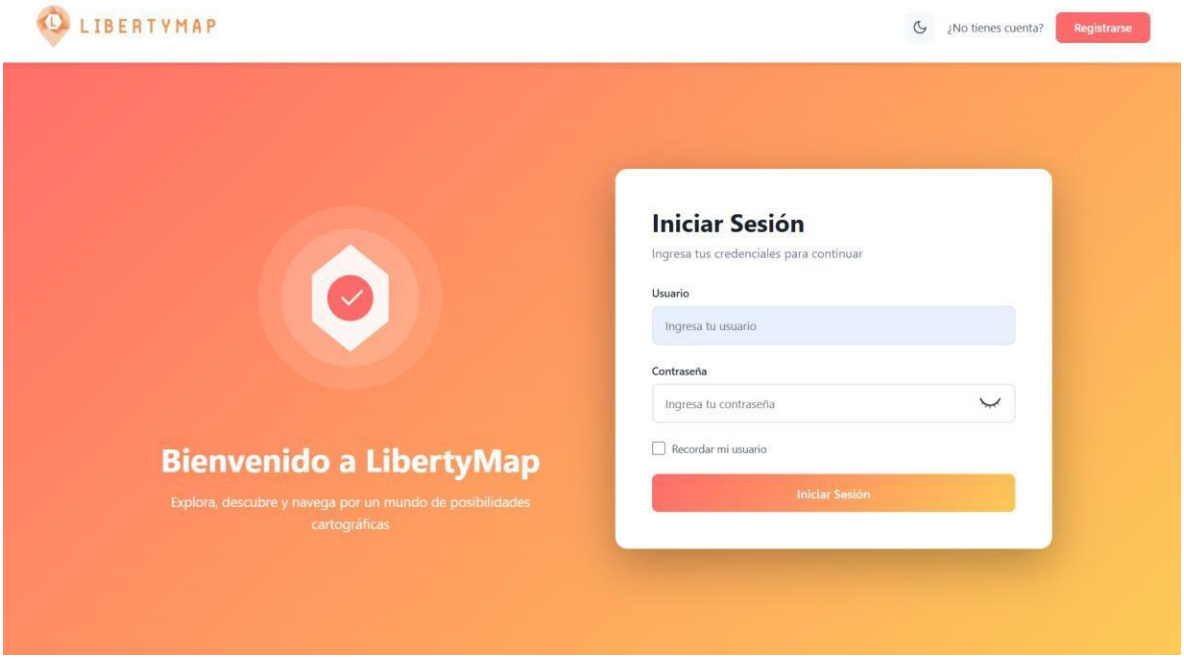

Esta es la primera ventana la cual contiene el mensaje de Bienvenida a nuestra página, para posteriormente ingresar a la página, además de eso puede cambiar el tono de la página con el botón de la luna en la esquina superior derecha te pedirá que ingreses con tu cuenta hacia la página y también puede habilitar el recordar usuario paras que una vez colocada tu cuenta ya no tengas que colocar el usuario la próxima vez que vuelva a entrar, de no ser así deberá dar clic en Regístrate aquí, para posteriormente pasar a el Registro de usuario.

Este botón sirve para cambiar a oscuro la página.

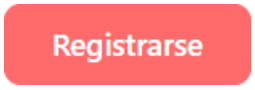

Te pedirá que ingreses con tu cuenta hacia la página, de no ser así deberá dar clic en Regístrate aquí, para posteriormente pasar a el Registro de usuario.

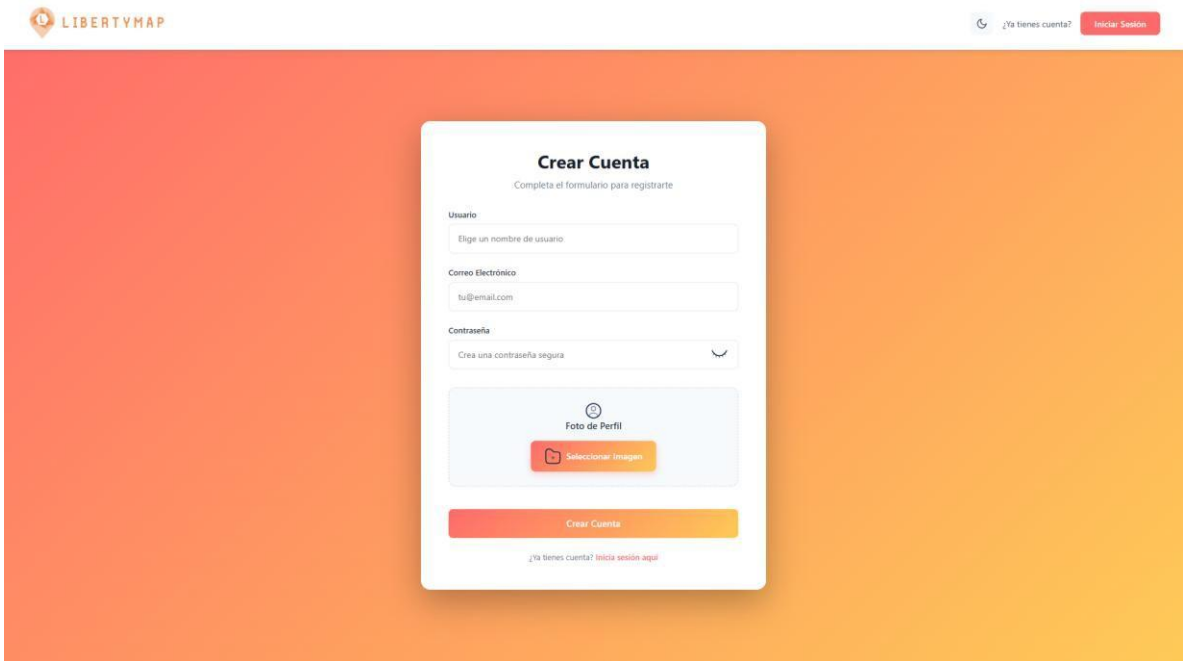

Deberás llenar cada campo solicitado como:

- Usuario: Nombre de usuario
- Correo: Correo electrónico
- Contraseña: Debe ser mínimo 8 caracteres, 1 Mayúscula, 1 Minúscula, 1 Numero y un carácter especial.
- Foto de perfil: subir una foto de perfil para tu cuenta(opcional)

Después de rellenar todos los campos se debe dar en Registrar y podrás entrar a la página directamente.

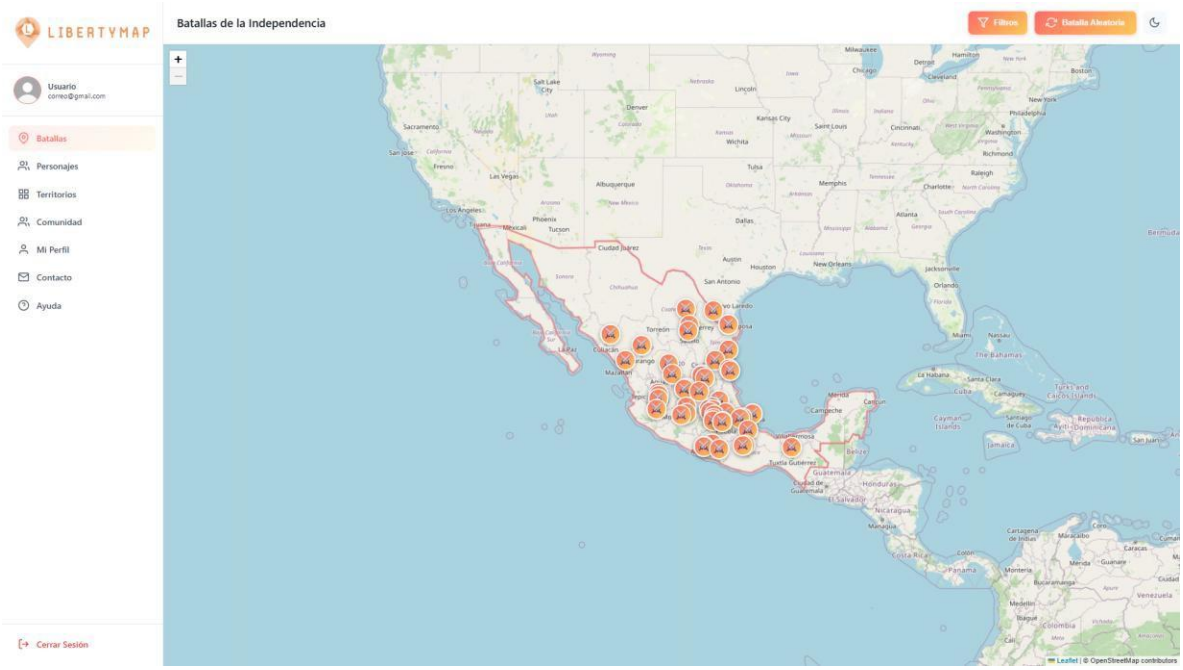

Esta ventana es la tercera de nuestra página web, aquí puede ver el mapa de México en el cual puede observar detalladamente las batallas sucedidas en la época de la independencia. **NO TODOS LOS ESTADOS TIENE UNA BATALLA.**

: Son todos los puntos donde hubo batallas, aquí puede darle clic y ver la información dada en el cuadro derecho.

Cuadro: Puedes ver la información de la batalla en el Estado seleccionada, también se muestra el nombre del Estado, la batalla descrita y 2 preguntas sobre esa batalla como los personajes involucrados o porque sucedió dicha batalla.

Control de zoom +/-: Sirve para poder dar un zoom hacia el mapa y verlo más detalladamente.

Aleatorio: Este botón sirve para que el mapa gire y te otorgue una batalla aleatoriamente.

Filtro: Este botón sirve para poder filtrar batallas y poder encontrar una en específico.

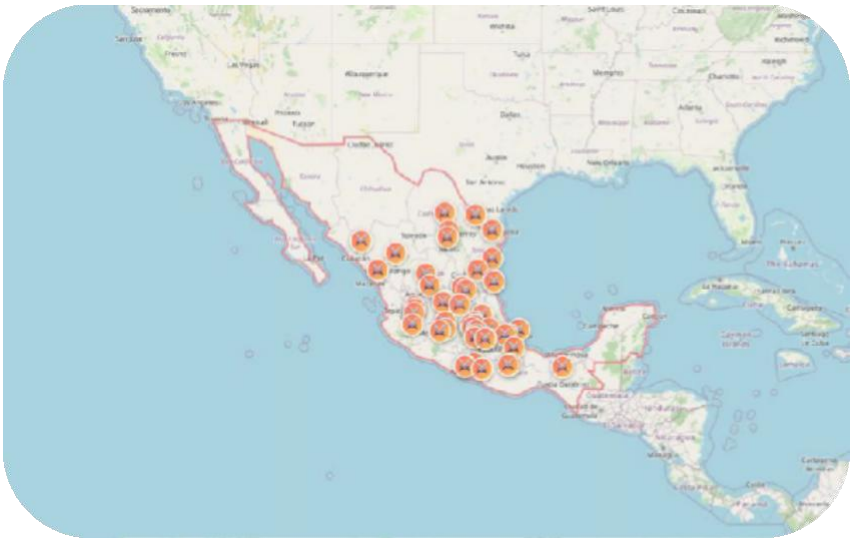

En la misma ventana al dar clic con el mouse en cada punto de batalla podemos ver todo lo que ocurrido con una breve explicación.

Cuadro de texto: Al haber dado clic con el mouse en alguno de los marcadores mostrados en el mapa, se mostrará el nombre de la Batalla. Posteriormente se mostrará la información de la batalla, personajes, estado, ciudad y las preguntas en el panel de la derecha; al dar clic en otro marcador en el mapa la información se actualizará.

Batalla de Tampico

Fecha: 27 de julio de 1829

Personajes: Isidro Barradas (español), Antonio Lopez de Santa Anna y Manuel Mier y Teran (mexicanos)

Ganador: Bando Insurgente

Ubicación: Tampico, Tamaulipas

Descripción: Aunque posterior a la independencia, fue clave: tropas españolas intentaron recuperar México por Tampico, pero fueron derrotadas.

Preguntas de Estudio

Pregunta 1: ¿Cuál fue la importancia estratégica del puerto para ambos bandos?

▸ Ver respuesta

Pregunta 2: ¿Cómo afectó al dominio realista en el noreste?

▸ Ver respuesta

Preguntas: Este apartado muestra dos preguntas acerca de la batalla con su respectiva respuesta, en donde al dar clic en “Ver respuesta” desplegará un panel con la respuesta**,** las preguntas varían dependiendo de cada Batalla incluyendo la respuesta.

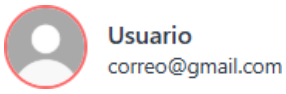

Este panel nos muestra la información de la cuenta del Usuario, con su correo y foto de perfil.

Personajes: Este botón te dirige a la ventana de Personajes**.**

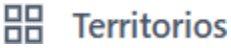

Territorios: Este botón te dirige a la ventana Mapa Comparativo.

Mi Perfil: Este botón te dirige a la ventana de El perfil de usuario.

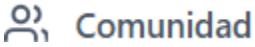

Comunidad: Este botón te dirige a la ventana de Comunidad.

Ayuda: Este botón te dirige al Manual de Usuario.

Cerrar sesión: Este botón cierra la sesión del usuario para que posteriormente sea dirigido a la ventana de saber un poco más sobre nosotros ahí podrás estas más informado sobre esta página y podrás crear una cuenta o iniciar sesión si quieres volver a ingresar a la página nuevamente.

Interfaces del Panel de Menú

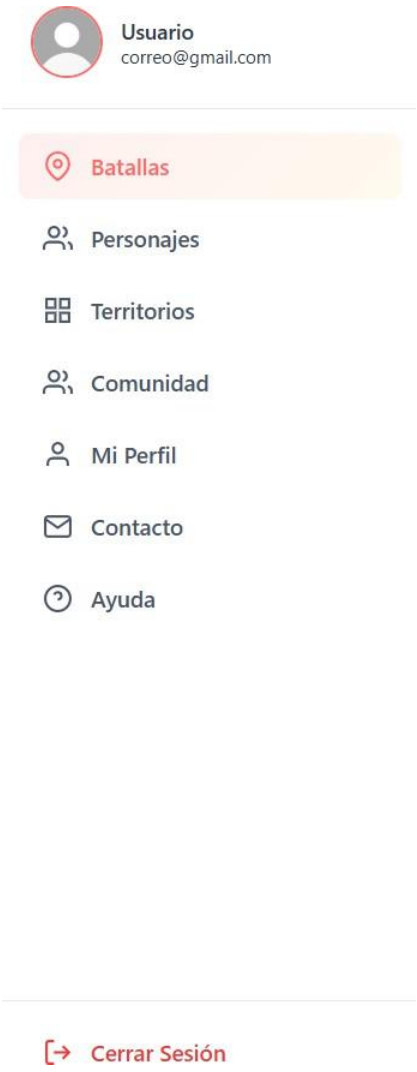

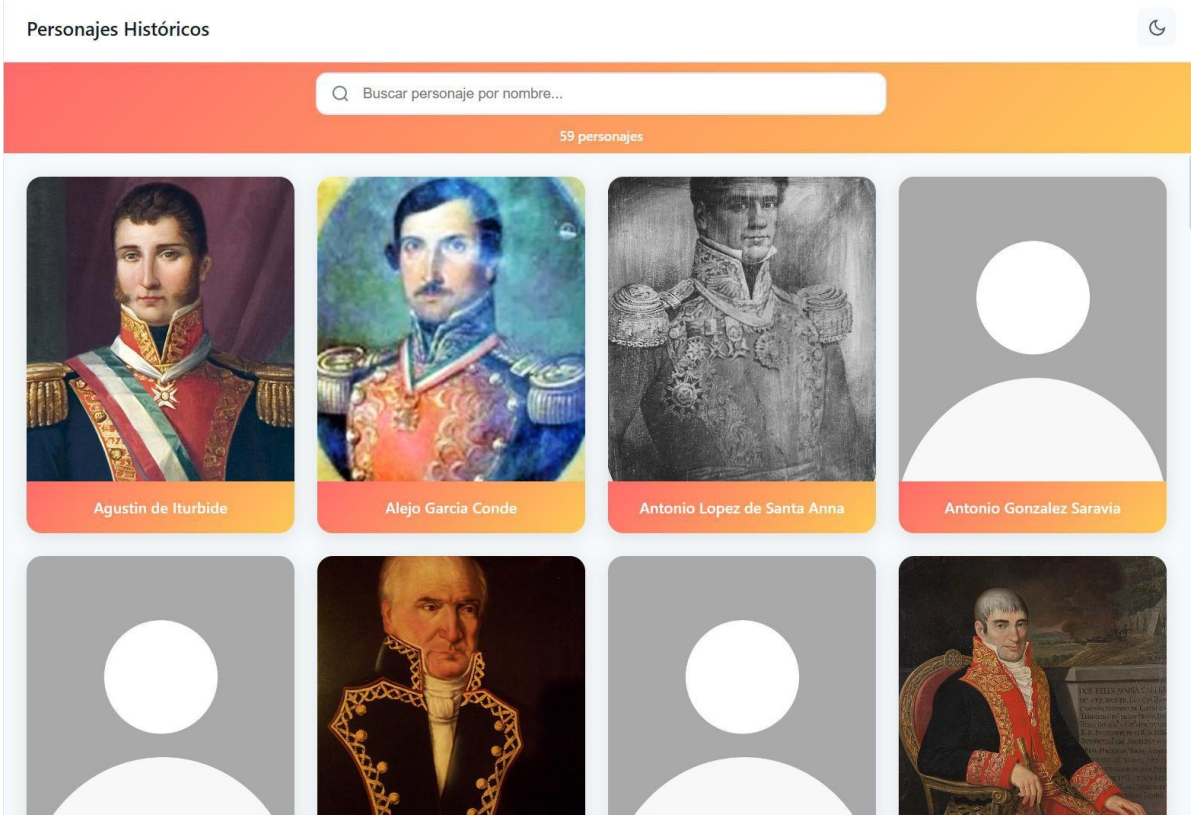

Esta ventana de Personajes, nos muestra cada personaje que estuvo involucrado en cada batalla con su descripción de quien fue, año de nacimiento y fallecimiento, junto con la fuente de consulta.

En el buscador, tienes la facilidad de encontrar el personaje mediante su nombre.

Al colocar el mouse sobre un personaje, nos dará su información correspondiente.

La ventana de Mapa comparativo, nos muestra, la imagen del territorio perdido en el año mostrado, junto con su Momento del suceso, Responsables, Situación anterior, Causas, Consecuencias y Fuente.

: Este botón sirve para cambiar a la siguiente situación de perdida de territorio

: Este botón sirve para cambiar a la anterior situación de perdida de territorio

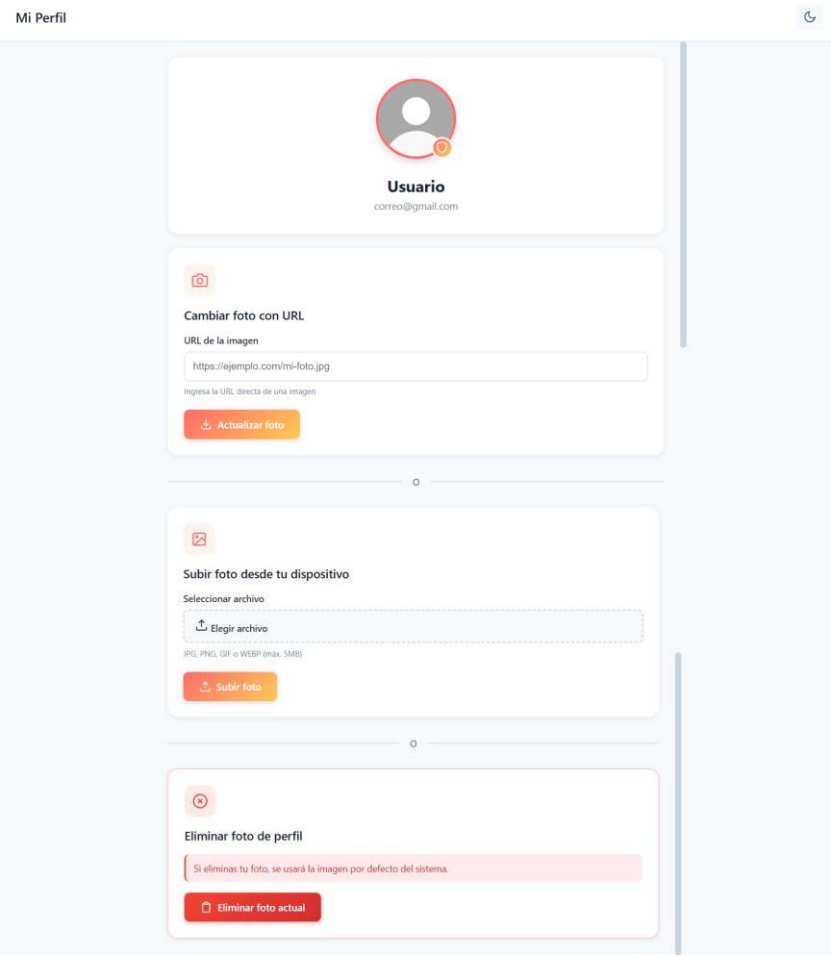

Esta ventana te muestra la opción de perfil el cual te enseña tu foto de perfil, usuario y correo electrónico colocado al crear la cuenta. Además, te da la opción de subir la foto si es que no colocaste al crear la cuenta y en caso de a ver puesto una eliminar la foto, ahí mismo esta el subir la foto mediante una url.

Ingresar la url de la imagen que desees.



Actualizar foto: Este botón hace que se actualice la foto después de colocar la url.

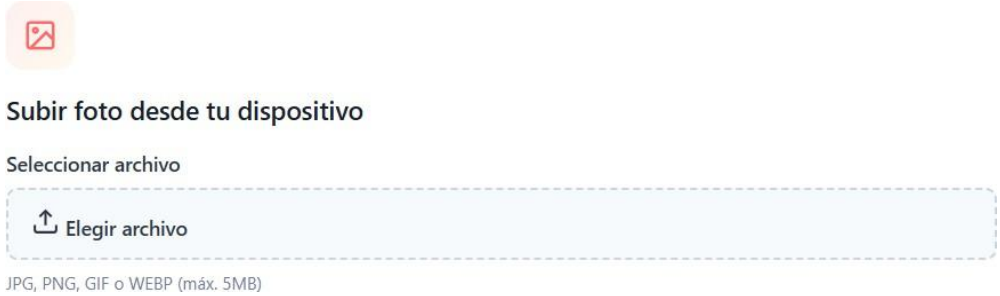

En caso de que cuentes con la foto dentro de tus archivos puedes seleccionarla y subirla.

Subir foto: Este botón es para subir la foto a tu perfil después de que la hayas seleccionado de archivos.

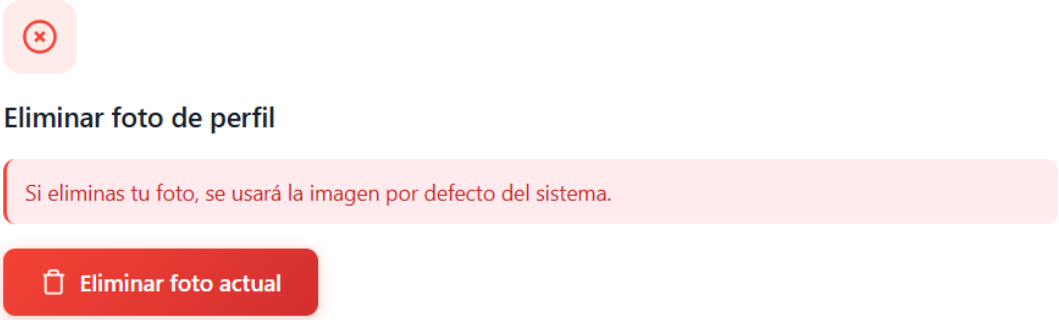

Eliminar foto actual: Este botón te permite eliminar la foto con la que cuentes actualmente.

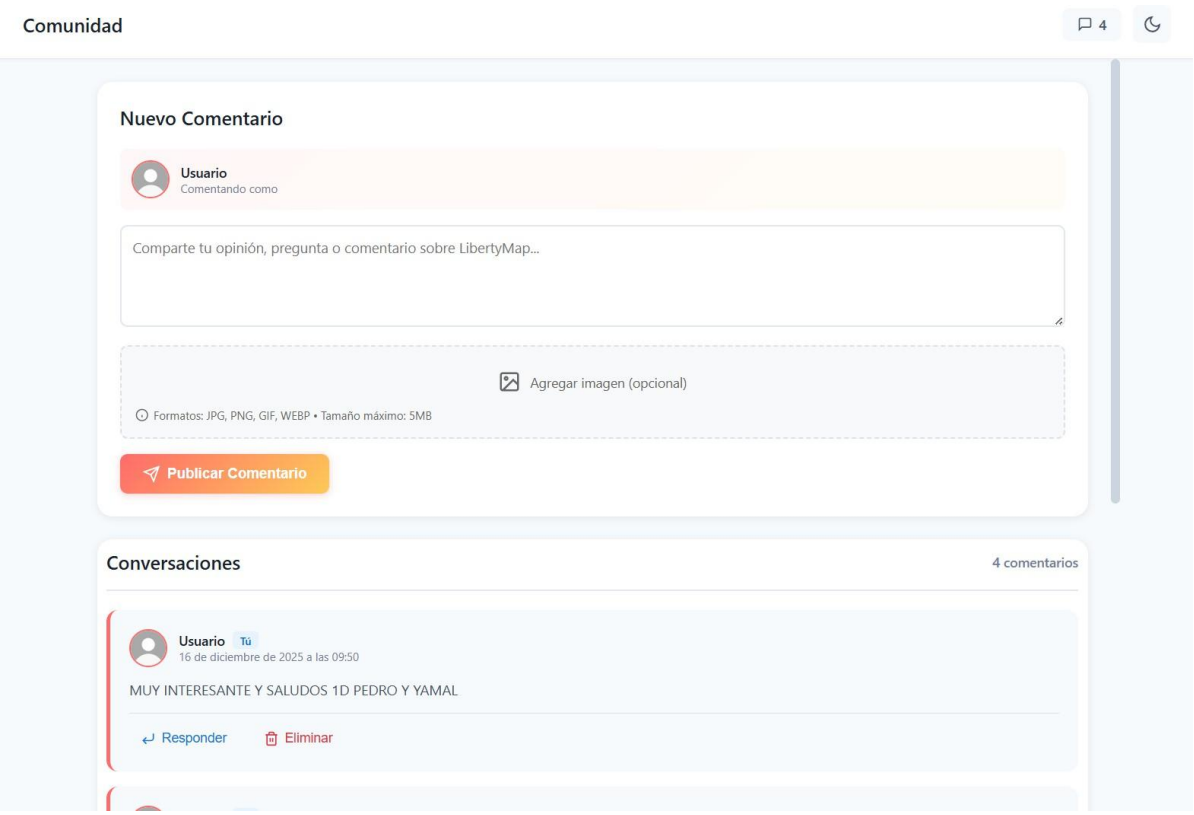

La ventana Comunidad, sirve para que el usuario comparta sus dudas, propuestas, ideas, comentarios y mejoras acerca de nuestra página web. En cada comentario se muestra el nombre de usuario, foto de perfil, fecha y hora a la que se publicó el comentario y en la sección de Comentarios de la Comunidad se ve cada usuario que allá comentado con la cantidad de comentarios enviados.

Aquí se ingresa el comentario que deseas subir a la página, solamente debes da clic en Escribe tu comentario aquí…, posteriormente se mostrara un mensaje si es que se subió correctamente o ingreso palabras que no sean permitidas por el filtro.

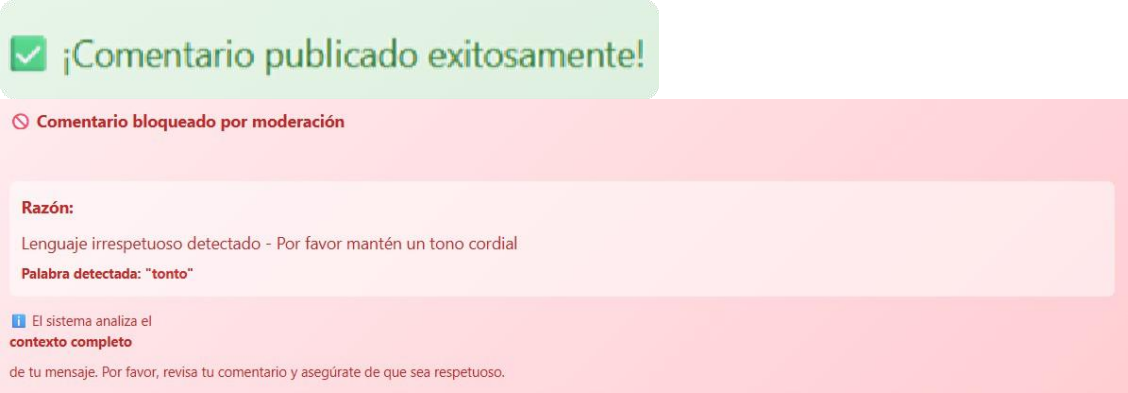

Este botón sirve para publicar el comentario.

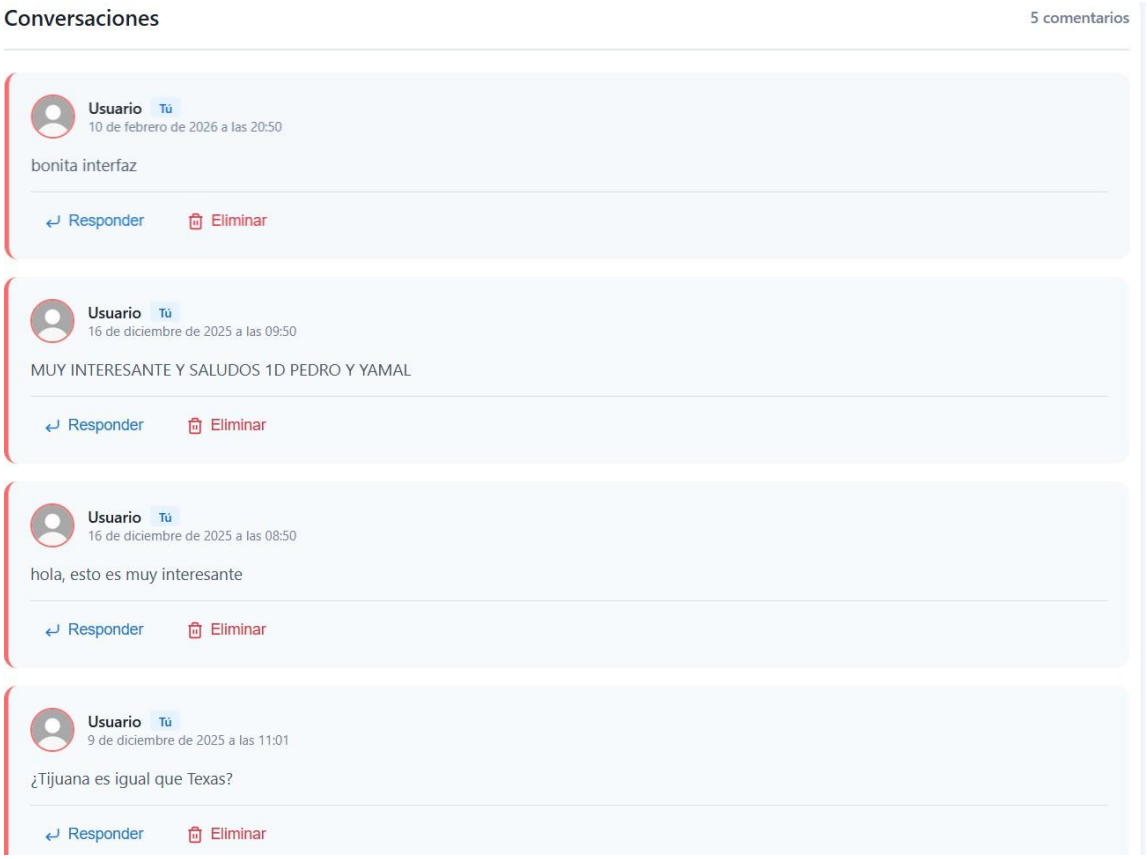

En la sección de Comentarios de la Comunidad se muestra la lista de comentarios de los usuarios junto con la cantidad de comentarios que se han publicado.

4.3 Posibles errores y su corrección

4.3.1 Errores

1. **Internet:** Necesitas Internet para llegar a usar nuestra página, si no, no cargara y no se mostrará el Mapa.

2. **Internet:** No mostrar el mapa de territorio.

3. **Sobrecarga de datos:** No poder enviar un cometario.

4. **Sobrecarga de datos:** No se muestren por completo la lista de comentarios.

5. **Información:** No mostrar la información completa de la batalla.

6. **Información:** No se muestre el usuario.

4.3.2 Corrección

1. **Internet:** Conectar tu dispositivo a Internet, mediante conexión inalámbrica o por cable.

2. **Internet:** Asegurarse de tener conexión a internet.

3. **Sobrecarga de datos:** Recarga/Refresca la página.

4. **Sobrecarga de datos:** Recarga/Refresca la página.

5. **Información:** Cerrar e iniciar sesión.

6. **Información:** Volver a selecciona la batalla para que se muestra completa la información.

NO CONTAMOS CON DEMAS ERRORES QUE LLEGASEN A SER POSIBLES DENTRO DE NUESTRA PAGINA WEB

4.4 Preguntas Frecuentes

- **¿Dónde debo de presionar para ver una batalla?**
  Para que puedas ver la información de las batallas debes de seleccionar la batalla que quieras ver dentro del mapa y presionar el icono el cual te dará la información.

- **¿Cómo funcionan los iconos?**
  Presionar en el icono hace que muestre toda la información de la batalla, con su Estado, Ciudad, personajes y se agregan también 2 preguntas junto con su respuesta correspondiente sobre esa batalla.

- **¿Cómo cambio de pregunta?**
  No puede hacer el cambio de la o las preguntas que se muestran, pero puede cambiar de batalla y ver otras preguntas con sus respuestas a dicha pregunta de la batalla.

- **¿Cómo puedo ver la respuesta de la pregunta?**
  Para que pueda ver las respuestas es muy sencillo lo único que debe de hacer es pasar el mouse o el puntero del mouse por la pregunta, eso arrojara las respuestas de inmediato y podrá saber más sobre la batalla.

- ¿Qué hago si no aparece mi usuario al iniciar sesión?
  Cierra sesión si quedó abierta en otra ventana, actualiza la página e intenta ingresar nuevamente. Si el problema continúa, vuelve a escribir tu correo y contraseña correctamente.

- ¿Qué sucede si olvidé mi contraseña?
  Por ahora la página no cuenta con recuperación automática de contraseña. Debe crear una cuenta nueva usando un correo distinto.

- ¿Por qué algunos estados no muestran batallas?
  Esto es normal. No todos los estados participaron en batallas de la Independencia, por eso algunos puntos del mapa no tienen información disponible.

- ¿Cómo funciona el botón Aleatorio?
  El botón selecciona una batalla al azar dentro del mapa y actualiza automáticamente el cuadro de información con su descripción, personajes y preguntas.

- ¿Por qué no puedo ver la imagen en el Mapa Comparativo?
  Asegúrese de tener buena conexión a internet. Si la imagen no carga, refresque la página.

- ¿Puedo cambiar mi foto de perfil?
  Actualmente la plataforma solo muestra la foto registrada inicialmente. No se puede cambiar desde el sistema.

- ¿Qué puedo escribir en la sección Comunidad?
  Puedes compartir dudas, sugerencias, mejoras o comentarios relacionados con la página. Los mensajes ofensivos o inapropiados no se publicarán.

- ¿Por qué mi comentario no se publicó?
  Puede ser por dos razones:
  - Escribiste palabras no permitidas.
  - El servidor tuvo una sobrecarga. En ese caso solo refresca la página e inténtalo de nuevo.

- ¿Cómo paso a la siguiente situación en el Mapa Comparativo?
  Debes presionar la flecha derecha (↷) para avanzar y la flecha izquierda (↶) para regresar a la situación anterior.

- ¿Qué hago si el mapa no me permite hacer zoom?
  Refresca la página. Si el problema sigue, revisa la conexión a internet o prueba desde otro navegador.

5. Datos de contacto

Autor 1
Miguel Alejandro Lerma Rosales
Correo: mike.lermar@gmail.com
Teléfono: 8342642153

Autor 2
Enrique Gerardo Olazaran Izaguirre
Correo: enrique.ola.iza@gmail.com
Teléfono: 8342511414

Autor 3
Leonardo Lopez Hinjosa
Correo: ardol930@gmail.com
Teléfono:8342562454

Asesor Técnico
Carlos Mario Balboa Casanova
Correo: carlosmario.balboa.cb271@dgeti.sems.gob.mx
Teléfono: 8341018594

Asesor Metodológico
Sergio Isauro Flores Vázquez
Correo: sergio_flores89@hotmail.com
Teléfono: 8341432268

6. BIBLIOGRAFIA

1. wikiHow. (2021, 30 julio). Cómo instalar Google Chrome: 10 Pasos (con imágenes). wikiHow. https://es.wikihow.com/instalar-Google-Chrome

2. Leaflet — an open-source JavaScript library for interactive maps. (s. f.-b). Recuperado de https://leafletjs.com/

3. Tutorials - Leaflet - a JavaScript library for interactive maps. (s. f.). Recuperado de https://leafletjs.com/examples.html

4. Oficina de Tecnología y Sistemas de Información. (2020). GUÍA PARA LA ELABORACIÓN DEL MANUAL DE USUARIO DE LOS SISTEMAS DE INFORMACIÓN. DEPARTAMENTO NACIONAL DE PLANEACION. Recuperado de https://drive.google.com/file/d/1P3odydzT0LcMoxDNJlMN90S_fjddMkHl/view